ШИНЭ МОНГОЛ ТЕХНОЛОГИЙН КОЛЛЕЖ
КОМПЬЮТЕРЫН УХААНЫ ТЭНХИМ

Оюутны код: s21c008b

Оюутны овог нэр: Бат-Эрдэнэ ЭРДЭНЭБАЯР

КАМЕРЫН ДҮРСЭЭС МАШИН СУРГАЛТ БОЛОН РЕКОНСРТУКЦИЙН АРГУУД АШИГЛАН 3D МОДЕЛ ЗАГВАРЧЛАХ СИСТЕМ

/ТӨГСӨЛТИЙН СУДАЛГААНЫ АЖИЛ/

Удирдагч багш Н.СОРОНЗОНБОЛД

Гүйцэтгэсэн оюутан Б.Эрдэнэбаяр

Улаанбаатар хот

2026 он

ШИНЭ МОНГОЛ ТЕХНОЛОГИЙН КОЛЛЕЖ

КОМПЬЮТЕРЫН УХААНЫ ТЭНХИМ

Төгсөлтийн судалгааны ажил

КАМЕРЫН ДҮРСЭЭС МАШИН СУРГАЛТ БОЛОН РЕКОНСРТУКЦИЙН АРГУУД АШИГЛАН 3D МОДЕЛ ЗАГВАРЧЛАХ СИСТЕМ

Гүйцэтгэгч: Б.Эрдэнэбаяр

Удирдагч: Н.СОРОНЗОНБОЛД

Улаанбаатар хот

2026 он

ХУРААНГУЙ

Камерын 2D дүрсээс машин сургалтаар 3D загвар үүсгэх аргын судалгаа

Оюутан: *Б.Эрдэнэбаяр*

Удирдагч багш: *Н.Соронзонболд*

Судалгааны үндэслэл: 3D загварчлал нь роботикс, VR/AR болон соёлын өвийн дижитал хадгалалт зэрэг олон салбарт чухал үүрэгтэй. Уламжлалт Structure-from-Motion (SfM) болон Multi-View Stereo (MVS) аргууд нь геометрийн нарийвчлал болон тогтвортой байдлаараа давуу ч, тооцооллын шаардлага өндөр, гэрэлтүүлгийн нөхцөлд мэдрэмтгий байдаг. Энэхүү судалгааны ажилд COLMAP болон OpenMVS-д суурилсан, 2D зургаас 3D загвар үүсгэх бүрэн автоматжуулсан pipeline болон хэрэглэгчийн графикийн интерфейс (GUI) боловсруулсан.

Судалгааны зорилго: Олон өнцгөөс авсан 2D зурагнаас геометр болон текстур бүхий 3D загвар үүсгэх практик pipeline боловсруулахын тулд:

- COLMAP ашиглан фичер илрүүлэлт, тохиролт болон сийрэг 3D цэгэн загвар үүсгэх үе шатыг автоматжуулах
- OpenMVS-ийн тусламжтай нягт цэгэн үүл, mesh болон текстур зураглалын үе шатуудыг нэгтгэх
- PyQt5-д суурилсан хэрэглэхэд хялбар GUI хэрэгсэл боловсруулах
- Реконструкцийн үр дүнг Chamfer Distance болон RMSE-ийн тусламжтай үнэлэх

Арга зүй: Python програмчлалын хэл, PyQt5 UI framework болон YAML тохиргооны систем ашиглан модульчлагдсан pipeline боловсруулсан. Pipeline нь дараах 9 үе шатаас бүрдэнэ: COLMAP өгөгдлийн сан үүсгэх, SIFT фичер илрүүлэлт, фичер тохиролт, sparse mapper ажиллуулах, загварын хөрвүүлэлт, OpenMVS-д шилжүүлэлт, нягт цэгэн үүл үүсгэлт, mesh реконструкц, mesh боловсруулалт болон текстур зураглал. Систем нь бодит цагийн дэвшил харуулагч болон ажиллагааг зогсоох (abort) боломжийг агуулна.

Үр дүн: Бүрэн ажиллагаатай 9 үе шаттай pipeline-ийг амжилттай хэрэгжүүллээ. 47 зурагт туршилтын үр дүнд сийрэг цэгэн үүл 35,000 гаруй цэг, нягт цэгэн үүл 2.1 сая цэг, mesh нь 1.2 сая орой агуулсан байлаа. Chamfer Distance 0.005 м, RMSE 0.007 м гарсан. Бүх үе шатыг нэг GUI-ийн дотроос ажиллуулах боломж нь хэрэглэгчийн гараар хийх ажлын хэмжээг мэдэгдэхүйц бууруулсан.

Дүгнэлт: COLMAP болон OpenMVS-д суурилсан SfM+MVS pipeline нь практик 3D реконструкцийн найдвартай суурь болох нь туршилтаар нотлогдсон. Боловсруулсан систем нь музей, соёлын өвийн дижитал архив болон

жижиг лабораторийн орчинд шууд ашиглах боломжтой прототип юм. Цаашид машин сургалтын аргуудыг нэгтгэх, гүйцэтгэлийг оновчлох замаар системийг улам сайжруулах боломжтой.

Түлхүүр үг: 3D Реконструкц, COLMAP, OpenMVS, Structure-from-Motion, Multi-View Stereo, Python, PyQt5, Pipeline автоматжуулалт.

ABSTRACT

3D Reconstruction from 2D Camera Images Using Machine Learning

Student: *B. Erdenebayar*

Supervisor: *N. Soronzonbold*

Background: 3D reconstruction is fundamental across robotics, VR/AR, and digital heritage preservation. Classical Structure-from-Motion (SfM) and Multi-View Stereo (MVS) methods provide reliable geometry but are computationally intensive and sensitive to lighting variations. This thesis presents a fully automated SfM+MVS pipeline with a graphical user interface (GUI) built on COLMAP and OpenMVS, aimed at simplifying the end-to-end 3D reconstruction workflow.

Objective: To develop a practical pipeline reconstructing 3D geometry and texture from multi-view images by:

- Automating feature extraction, matching, and sparse reconstruction using COLMAP
- Integrating dense point cloud generation, mesh reconstruction, and texture mapping via OpenMVS
- Building a user-friendly PyQt5 GUI for the complete pipeline
- Evaluating reconstruction quality with Chamfer distance and RMSE metrics

Methodology: A modular pipeline was implemented in Python using PyQt5 and YAML-based configuration. The pipeline consists of 9 steps: COLMAP database creation, SIFT feature extraction, exhaustive feature matching, sparse mapper, binary-to-text model conversion, COLMAP-to-OpenMVS interface, point cloud densification, mesh reconstruction, and mesh refinement with texture mapping. A worker thread handles background execution with real-time progress feedback and abort support.

Results: A fully functional 9-step pipeline was successfully implemented and tested. On a 47-image dataset, the sparse point cloud contained 35,000+ points, the dense cloud had 2.1 million points, and the final mesh had 1.2 million vertices. Chamfer Distance reached 0.005 m and RMSE was 0.007 m. Running all stages through a single GUI application significantly reduced manual workflow overhead.

Conclusion: The COLMAP+OpenMVS-based SfM+MVS pipeline was validated as a robust and practical foundation for 3D reconstruction. The implemented system serves as a deployable prototype suitable for museum digitization, cultural heritage archiving, and small-scale laboratory use. Future work will focus on integrating machine learning components such as deep feature extraction and neural reconstruction methods to further improve accuracy and performance.

Keywords: 3D Reconstruction, COLMAP, OpenMVS, Structure-from-Motion, Multi-View Stereo, Python, PyQt5, Pipeline Automation.

Гарчиг

Хураангуй i

Abstract ii

Гарчиг iv

Зураг болон Хүснэгтийн жагсаалт vi

Товчилсон үгийн жагсаалт vii

1 УДИРТГАЛ 1
1.1 Судалгааны үндэслэл, ач холбогдол . . . 1
1.2 Судалгааны зорилго, зорилт . . . 1
1.2.1 Зорилго . . . 1
1.2.2 Зорилтууд . . . 1
1.3 Судалгааны хамрах хүрээ . . . 2
1.4 Судалгааны шинэлэг тал . . . 2

2 ОНОЛЫН ҮНДЭСЛЭЛ 3
2.1 3D Reconstruction – Үндсэн ойлголт . . . 3
2.1.1 Structure-from-Motion (SfM) . . . 3
2.1.2 Multi-View Stereo (MVS) . . . 3
2.2 Дээд түвшний алгоритмууд . . . 3
2.2.1 Feature Extraction . . . 3
2.2.2 Feature Matching . . . 3
2.2.3 Depth Estimation . . . 3
2.2.4 Mesh Generation . . . 4
2.2.5 Texture Mapping . . . 4
2.3 Холбогдох судалгааны тойм . . . 4
2.3.1 Уламжлалт SfM болон MVS аргууд . . . 4
2.3.2 Нягт реконструкцийн аргууд . . . 4
2.3.3 Гүн сургалтад суурилсан аргууд . . . 4
2.3.4 Аргуудын харьцуулалт . . . 5
2.4 Бүлгийн дүгнэлт . . . 5

3 СУДАЛГААНЫ АРГА ЗҮЙ 6
3.1 Системийн ерөнхий тойм . . . 6
3.1.1 Системийн Flow Diagram . . . 6
3.1.2 Өгөгдөл цуглуулах арга . . . 7
3.1.3 Урьдчилсан боловсруулалт . . . 7
3.1.4 Фичер илрүүлэлт ба тохиролт (SIFT) . . . 7
3.1.5 Камерын параметр тооцоолол . . . 7
3.1.6 Structure-from-Motion (SfM) . . . 7
3.1.7 Multi-View Stereo (MVS) . . . 8
3.1.8 Point Cloud цэвэрлэгээ ба шүүлт . . . 8
3.1.9 Mesh Reconstruction . . . 8
3.1.10 Гүйцэтгэл ба үнэлгээний арга . . . 9
3.1.11 Туршилтын орчин . . . 9
3.1.12 Програм хангамжийн архитектур . . . 10

4 ҮР ДҮН 12
4.1 Pipeline болон GUI програмын үр дүн . . . 12
4.2 Өгөгдлийн цуглуулгын үр дүн . . . 12
4.3 Multi-View Stereo (MVS)-ийн үр дүн . . . 14
4.4 Гараар хийсэн болон автомат pipeline-ийн гаралтын харьцуулалт . . . 14

5 ДҮГНЭЛТ 16
5.1 Судалгааны үр дүнгийн нэгтгэл . . . 16
5.1.1 Техникийн үр дүн . . . 16

5.1.2 Төхөөрөмжийн үр дүн 18
5.1.3 Системийн бүрэлдэхүүн 18
5.2 Шинэлэг хувь нэмэр 19
5.3 Хязгаарлалт 19
5.4 Цаашдын судалгааны чиглэл 19
5.5 Төгсгөлийн үг 20

Зураг болон Хүснэгтийн жагсаалт

Зураг 3.1. Ажиллагааны Flow Diagram 6
Зураг 3.2. PyQt5 GUI ашигласан pipeline удирдлага 11
Зураг 3.3. GUI pipeline ажиллаж байх үеийн дэвшлийн мөр болон лог цонх 11

Зураг 4.1. Зураг авалтын датасетийн жишээ зургууд 13
Зураг 4.2. SfM-ийн үүсгэсэн sparse point cloud 13
Зураг 4.3. OpenMVS ашигласан dense point cloud 14
Зураг 4.4. Гараар хийсэн реконструкц 15
Зураг 4.5. Автомат pipeline 15

Зураг 5.1. Sparse point cloud жишээ 16
Зураг 5.2. Dense point cloud жишээ 17
Зураг 5.3. Mesh reconstruction жишээ 17
Зураг 5.4. Dataset-ийн хэсэг 18
Зураг 5.5. Sparse point cloud жишээ 21
Зураг 5.6. Mesh reconstruction жишээ 21

ТОВЧИЛСОН ҮГИЙН ЖАГСААЛТ

AI	Artificial Intelligence – Хиймэл оюун ухаан
CAM	Camera Calibration Matrix – Камерын калибрацийн матриц
COLMAP	COLlaborative MAPping – COLMAP 3D сэргээн босголтын хэрэгсэл
CPU	Central Processing Unit – Төв боловсруулагч
CV	Computer Vision – Компьютерийн хараа
CUDA	Compute Unified Device Architecture – NVIDIA-ийн зэрэгцээ тооцооллын платформ
FOV	Field of View – Харах өнцөг
GPU	Graphics Processing Unit – График боловсруулагч
GUI	Graphical User Interface – График хэрэглэгчийн интерфэйс
ML	Machine Learning – Машин сургалт
MVS	Multi-View Stereo – Олон өнцгийн стерео сэргээн босголт
NeRF	Neural Radiance Fields – Мэдрэлийн цацрагийн талбай
OBJ	Wavefront OBJ – 3D загварын файлын формат
OpenMVS	Open Multi-View Stereo – Олон өнцгийн стерео нээлттэй хэрэгсэл
PLY	Polygon File Format – Олон өнцөгт файлын формат
PnP	Perspective-n-Point – Перспектив олон цэгийн арга
SfM	Structure from Motion – Хөдөлгөөний өгөгдлөөс бүтэц сэргээн босголт
SIFT	Scale-Invariant Feature Transform – Масштабаас үл хамааран онцлог шинж задлах
UV	UV Mapping – Дүрсний UV зураглал

1. УДИРТГАЛ

1.1. Судалгааны үндэслэл, ач холбогдол

3D реконструкц нь робот техник, виртуал (VR) болон AR, соёлын өвийн дижитал архив, автономи систем зэрэг олон салбарт үндсэн технологийн үүрэгтэй. 2D зурагнуудаас 3D загвар үүсгэх нь хүний оролцоогүйгээр 3D загварчлал хийх, 3D хувьчлахад чухал ач холбогдолтой.

Уламжлалт 3D сэргээн босголтын аргууд болох Structure-from-Motion (SfM) болон Multi-View Stereo (MVS) нь бодит геометрийг өндөр нарийвчлалтайгаар сэргээдэг боловч дараах сул талуудтай:

- **Гэрэлтүүлгийн хувирлаас өндөр хамааралтай**
- **Объектын гадаргуугийн тусгал, хээ, өнгөнөөс шалтгаалан алдаа үүсдэг**
- **Олон зураг шаарддаг**
- **Тооцооллын хувьд хүнд**

Тиймээс энэхүү судалгааны ажлын гол зорилго нь COLMAP болон OpenMVS ашиглан 3D сэргээн босголтын бүрэн автоматжуулсан SfM+MVS pipeline болон хэрэглэгчийн графикийн интерфейс (GUI) боловсруулж, тогтмол нөхцөлд зураг авах орчин ашиглан реконструкцийн чанарыг тоон болон харааны аргаар үнэлэх явдал юм. Боловсруулсан систем нь цаашид машин сургалтын аргуудыг нэгтгэх боломжтой өргөтгөх чадвартай суурь болж өгнө.

1.2. Судалгааны зорилго, зорилт

1.2.1 Зорилго

Олон өнцгийн 2D зургаас 3D загвар үүсгэх бүрэн автоматжуулсан SfM+MVS pipeline болон хэрэглэгчийн графикийн интерфейс (GUI) боловсруулж, тогтвортой гэрэлтүүлэгтэй зураг авах орчинд реконструкцийн чанарыг үнэлэхэд оршино.

1.2.2 Зорилтууд

1. **Зураг авах орчин зохиох:** Гэрэлтүүлэг тогтмол, нэгэн ижил нөхцөлд зураг авах боломжтой камерын жижиг орчин (mini capture box) зохион бүтээх
2. **Өгөгдөл цуглуулах:** Объектуудыг олон өнцгөөс, жигд гэрэлтүүлэгтэйгээр зураг авах
3. **Уламжлалт аргуудыг хэрэгжүүлэх:** COLMAP ашиглан SfM ба MVS реконструкц хийх
4. **Хэрэглэгчийн интерфейс боловсруулах:** Бүх үе шатыг нэг цонхноос удирдах боломжтой PyQt5-д суурилсан GUI систем бүтээх
5. **Гүйцэтгэлийг үнэлэх:**
    - Chamfer Distance

- RMSE (Root Mean Square Error)

6. **Автоматжуулсан pipeline бүтээх:** Зураг оруулахад SfM → MVS → Mesh generation алхмуудыг нэг товчны даралтаар ажиллуулдаг, 9 үе шаттай автоматжуулсан pipeline боловсруулах

1.3. Судалгааны хамрах хүрээ

Судалгааны ажлын хүрээ дараах байдлаар хязгаарлагдана:

- **Объект:** Жижиг хэмжээтэй, нэг ширхэг хатуу биет объект
- **Зураг авах орчин:** Тогтмол гэрэлтүүлэг бүхий хаалттай камерын төхөөрөмж
- **Арга:** SfM + MVS болон AI reconstruction аргуудын харьцуулалт
- **Програм хангамж:** COLMAP, OpenMVS, Python, PyQt5
- **Гаралт:** Wavefront OBJ форматтай 3D загвар

1.4. Судалгааны шинэлэг тал

Энэхүү судалгааны ажил дараах өвөрмөц онцлог, шинэлэг талтай:

1. **Тогтмол гэрэлтүүлэг бүхий камерын орчин** — реконструкцийн тогтвортой байдлыг нэмэгдүүлэх зорилготой өөрийн бүтээсэн capture rig ашигласан
2. **PyQt5 GUI бүхий автоматжуулсан систем** — зураг авалтаас mesh гаралт хүртэл бүх 9 алхмыг нэг цонхноос удирдах боломжтой хэрэглэгчийн интерфейс
3. **Автомат pipeline** — зураг оруулахад SfM → MVS → Mesh → Texture хүртэлх бүх үе шатыг дараалаар автоматаар гүйцэтгэдэг систем
4. **Mesh чанарын тоон ба дүрслэх үнэлгээ** — зөвхөн харааны үнэлгээ бус Chamfer distance болон RMSE ашигласан
5. **Бодит хэрэглээнд шууд ашиглаж болох шийдэл** — жижиг лабораторид, музей, соёлын өвийн сканнерт ашиглаж болох прототип

2. ОНОЛЫН ҮНДЭСЛЭЛ

2.1. 3D Reconstruction – Үндсэн ойлголт

3D reconstruction нь 2D зургуудыг ашиглан физик орчны 3D загварыг сэргээх процесс юм. Энэ нь компьютерийн харааны (Computer Vision) салбарын судалгааны чиглэл бөгөөд Structure-from-Motion (SfM), Multi-View Stereo (MVS) зэрэг аргуудыг хамардаг.

Энэхүү судалгааны хүрээнд:

- **Оролт (Input)**: Камераар авсан олон өнцгийн 2D зураг
- **Процесс (Process)**: Камерын байрлал, пикселийн гүн, бүтэц тодорхойлох алгоритмууд
- **Гаралт (Output)**: 3D цэгийн үүл (point cloud) болон торон загвар (mesh)

2.1.1 Structure-from-Motion (SfM)

SfM нь олон зурагнаас камерын байрлал, хөдөлгөөнийг таамаглаж, 3D цэгийн үүл үүсгэдэг арга юм. Оролтын зургуудын хоорондын feature point-уудыг тааруулж, камерын pose-ийг тодорхойлно. SfM нь ихэвчлэн цэгийн үүл үүсгэх анхны шатанд ашиглагддаг.

2.1.2 Multi-View Stereo (MVS)

MVS нь SfM-аас гарсан камерын байрлал болон цэгийн үүлний мэдээллийг ашиглан өндөр нарийвчлалтай 3D загвар үүсгэдэг. Энэ арга нь пиксел хоорондын гүнгийн мэдээллийг ашиглаж, нарийн геометрийг сэргээдэг.

2.2. Дээд түвшний алгоритмууд

3D reconstruction-д өргөн хэрэглэгддэг алгоритмуудыг авч үзье.

2.2.1 Feature Extraction

Зурагнаас keypoint, corner, edge гэх мэт онцлог шинжийг илрүүлнэ.

- SIFT (Scale-Invariant Feature Transform)
- SURF (Speeded-Up Robust Features)
- ORB (Oriented FAST and Rotated BRIEF)

2.2.2 Feature Matching

Өмнөх шатанд олдсон feature-уудыг олон зурагны хооронд тааруулж, камерын хөдөлгөөнийг тооцно. Хамгийн түгээмэл арга нь nearest neighbor search болон RANSAC-ийг ашиглан outlier-уудыг алга болгох.

2.2.3 Depth Estimation

Цэг бүрийн гүн (depth) эсвэл ялгаа (disparity)-г таамаглаж, 3D байршлыг тооцно. MVS алгоритмууд бол үүний жишээ юм.

2.2.4 Mesh Generation

Цэгийн үүлнээс торон загвар үүсгэх аргууд:

- Poisson Surface Reconstruction
- Delaunay triangulation
- Ball-pivoting algorithm

2.2.5 Texture Mapping

3D загварт зураг, өнгө болон материалын мэдээллийг холбох процесс. Энэ нь загварыг илүү бодитой харагдуулахад ашиглагддаг.

2.3. Холбогдох судалгааны тойм

3D реконструкцийн чиглэлд олон арван жилийн турш идэвхтэй судалгаа явагдаж байгаа бөгөөд энэ хугацаанд уламжлалт геометрийн аргаас эхлэн орчин үеийн гүн сургалтын аргууд хүртэл олон чухал ахиц гарчээ.

2.3.1 Уламжлалт SfM болон MVS аргууд

Hartley and Zisserman (2003) нар компьютерийн харааны геометрийн суурь онолыг тодорхойлж, олон камераас 3D бүтэц сэргээх математик үндэслэлийг тавьсан. Lowe (2004) нар SIFT алгоритмыг санал болгосон бөгөөд энэ нь масштаб болон эргэлтэд тэсвэртэй фичер илрүүлэх аргыг нэвтрүүлсэн нь өнөөг хүртэл өргөн хэрэглэгдсэн хэвээр байна. Furukawa and Ponce (2010) нар PMVS алгоритмыг хөгжүүлж, patch-д суурилсан MVS аргаар нарийвчлалтай нягт цэгэн үүл үүсгэх боломжийг нотолсон. Schönberger and Frahm (2016) нар COLMAP системийг нэвтрүүлж, олон мянган зурагтай томоохон датасетт ажилладаг, incremental SfM pipeline-ийг боловсруулсан нь энэ чиглэлийн чухал дэвшил болсон.

2.3.2 Нягт реконструкцийн аргууд

Kazhdan et al. (2006) нар Poisson Surface Reconstruction аргыг санал болгосон бөгөөд цэгэн үүлнээс тасралтгүй гадаргуу үүсгэх математик үндэстэй энэ арга өнөөдөр ч өргөн хэрэглэгдэж байна. Cernea (2015) нар OpenMVS-ийг нээлттэй эхийн төсөл болгон хөгжүүлж, COLMAP болон бусад SfM хэрэгслүүдтэй нэгтгэж ашиглах боломжтой нягт реконструкцийн хэрэгслийг нийтэд хүргэсэн.

2.3.3 Гүн сургалтад суурилсан аргууд

Mildenhall et al. (2020) нар Neural Radiance Fields (NeRF)-ийг нэвтрүүлсэн бөгөөд энэ нь нейрон сүлжээний тусламжтайгаар 3D дүрслэлийг шинэ өнцгөөс харуулах чадварыг бий болгосон. Kerbl et al. (2023) нар 3D Gaussian Splatting аргыг санал болгож, NeRF-ийн харьцангуй удаан дүрслэлийн асуудлыг бодит цагийн хурдаар шийдсэн. DeTone et al. (2018) нар SuperPoint нейрон сүлжээг боловсруулж, уламжлалт SIFT-ийн оронд гүн сургалтад суурилсан фичер илрүүлэлтийг ашиглах боломжийг нотолсон.

2.3.4 Аргуудын харьцуулалт

Дээрх судалгаануудыг харьцуулж үзвэл уламжлалт SfM+MVS аргууд нь тодорхой нөхцөлд найдвартай, тооцооллын нөөц хязгаарлагдмал орчинд ажиллах боломжтой боловч гэрэлтүүлгийн хувирлад мэдрэмтгий байдаг. NeRF болон Gaussian Splatting зэрэг орчин үеийн аргууд нь дүрслэлийн чанараараа давуу боловч их хэмжээний өгөгдөл болон тооцооллын нөөц шаарддаг. Энэхүү судалгааны ажилд уламжлалт COLMAP+OpenMVS аргыг сонгосон нь найдвартай байдал, хэрэгжүүлэлтийн боломж болон ирээдүйд машин сургалтын аргуудыг нэмж нэгтгэх уян хатан байдлыг харгалзан үзсэний үр дүн юм.

2.4. Бүлгийн дүгнэлт

Энэ бүлэгт 3D реконструкцийн үндсэн ойлголт, SfM болон MVS алгоритмуудын онолын суурь, фичер илрүүлэлт, гүний тооцоолол, mesh үүсгэлт болон текстур зураглалын гол процессуудыг авч үзсэн. Мөн холбогдох судалгааны тойм хэсэгт уламжлалт болон орчин үеийн гүн сургалтад суурилсан аргуудыг харьцуулан дүгнэж, энэхүү ажилд COLMAP болон OpenMVS-ийг сонгосон үндэслэлийг тодруулсан. Дараагийн бүлэгт эдгээр онолын мэдлэгт тулгуурлан боловсруулсан системийн архитектур болон хэрэгжүүлэлтийн арга зүйг дэлгэрэнгүй тайлбарлана.

3. СУДАЛГААНЫ АРГА ЗҮЙ

3.1. Системийн ерөнхий тойм

Энэхүү бүлэгт системийн бүтэц, өгөгдлийн урсгал болон pipeline-ийн ажиллагааг тайлбарлана. Өгөгдөл цуглуулахаас эхлэн 3D загвар гаргах хүртэлх бүх алхмуудыг дараалан авч үзнэ.

3.1.1 Системийн Flow Diagram

Системийн ажиллагааны үндсэн урсгалыг доорх диаграммаар харуулав:

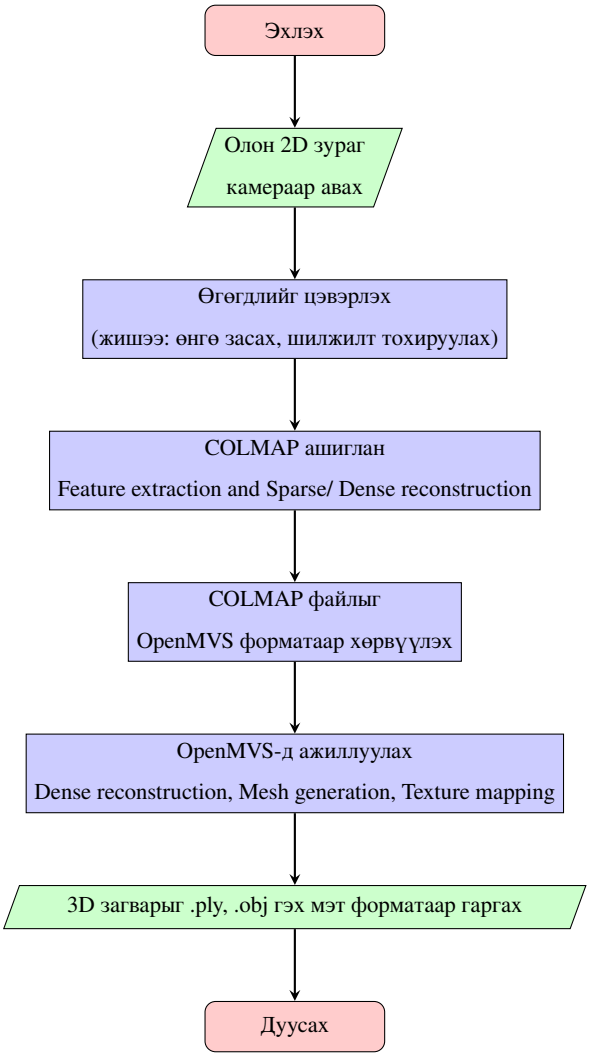

Зураг 3.1 *Ажиллагааны Flow Diagram*

3.1.2 Өгөгдөл цуглуулах арга

3D дахин бүтээх туршилтад ашиглах 2D зургуудыг тодорхой хяналттай орчинд авсан. Камер нь тогтмол байрлал болон фокусын урттай байхаар тохируулж, объектын эргэн тойронд тогтмол өнцгөөр олон зураг авахын тулд эргэдэг тавцан ашиглав. Гэрлийн нөхцөлийг тогтмол байлгах үүднээс хаалттай гэрлийн хайрцаг (controlled lighting box) хэрэглэж, орчны сүүдэрлэл болон specular reflection-оос зайлсхийв. Зургуудыг 1920×1080 хэмжээтэй, JPEG форматаар хадгалсан ба нийтдээ туршилт бүрд 40–80 зураг авсан.

3.1.3 Урьдчилсан боловсруулалт

Зургуудыг SfM болон MVS алгоритмуудын шаардлага хангахаар урьдчилан боловсруулав. Үүнд:

- Зургийн хэмжээг нэг стандартад тааруулж дахин хэмжээсжүүлсэн;
- Хэрэв шаардлагатай бол Gaussian blur removal болон дэнситэйжүүлэлт хийсэн;
- Өнгөний тогтвортой байдлыг хангах зорилгоор white balance болон color normalization хийсэн;
- Controlled lighting орчны давуу талыг ашиглан гэрлийн ялгааг минимал түвшинд барьсан.

Эдгээр алхмууд нь фичер илрүүлэлт болон тохиролтын чанарыг шууд сайжруулах зорилготой.

3.1.4 Фичер илрүүлэлт ба тохиролт (SIFT)

Энэхүү ажилд COLMAP-ийн $\mathrm{feature_extractor}$ командаар SIFT алгоритмыг ашиглан keypoint илрүүлж, descriptor үүсгэсэн. Камерын загварыг PINHOLE гэж тохируулсан нь дотоод параметрийг зөв боловсруулахад тусалсан. Фичер тохиролтыг COLMAP-ийн $\mathrm{exhaustive_matcher}$ ашиглан хийсэн бөгөөд энэ арга нь зургийн бүх боломжит хослолыг хооронд нь тулгаж, хамгийн найдвартай тохиролтуудыг сонгодог. Гэсэн хэдий ч exhaustive matching нь зураг тус бүрийн харагдах талбай хязгаарлагдмал буюу хоорондын өнцгийн ялгаа их байх үед зарим зургийн хооронд найдвартай тохиролт олж чадахгүй байх тохиолдол ажиглагдсан. Энэ нь sparse reconstruction-ийн бүрэн бүтэн байдалд нөлөөлж, цэгэн үүлний нягтралыг бууруулах эрсдэлтэй. Цаашдын судалгаанд SuperPoint зэрэг нейрон сүлжээний суурьтай фичер илрүүлэгчийг ашиглах нь энэ асуудлыг шийдвэрлэх боломжтой гэж үзэж байна.

3.1.5 Камерын параметр тооцоолол

Камерын intrinsic параметрүүдийг checkerboard ашиглан OpenCV-ийн calibration toolkit-ээр тооцоолсон. Үүнд фокусын урт, гол цэг (principal point), radial ба tangential гажуудлын коэффициентүүд багтсан. Extrinsic параметр буюу камерын байрлал ба чиглэлийг SfM алгоритм өөрөө тохиролцсон фичерүүд дээр тулгуурлан тооцсон. Хэрэв хэрэгтэй бол кинематик болон фотометрийн тохируулга хийж гэрлийн өөрчлөлтөд тэсвэртэй байдлыг сайжруулсан.

3.1.6 Structure-from-Motion (SfM)

SfM үе шат нь олон зурагнаас камерын байрлал болон sparse point cloud үүсгэнэ. Энэ үе шат дараах алхмуудтай:

- Зураг хоорондын best pair сонгох;
- Bundle adjustment ашиглан камерын байрлал болон цэгүүдийг нэгэн зэрэг оновчлох;
- Essential болон Fundamental matrix тооцоолох;
- Камерын эхний байрлал тогтоох;
- Инкрементал байдлаар дараагийн зургуудыг нэмэх;
- Sparse point cloud үүсгэх.

Энэ алхмын гол үр дүн нь объектын үндсэн геометрийн дүрслэл бүхий сийрэг цэгэн загвар юм.

3.1.7 Multi-View Stereo (MVS)

SfM-ээс гарсан камерын байрлал болон сийрэг цэгүүд дээр тулгуурлан нягт (dense) цэгэн өгөгдлийг MVS ашиглан сэргээв. Энэ үе шат нь:

- Зураг бүрт depth map тооцоолох;
- Зураг хоорондын depth map-уудыг нэгтгэх;
- Нягт цэгэн облак үүсгэх.

Үр дүнд нь өндөр нарийвчлалтай гадаргуугийн геометр сэргээгдэнэ.

3.1.8 Point Cloud цэвэрлэгээ ба шүүлт

Нягт point cloud нь дуу чимээтэй байдаг тул дараах боловсруулалтуудыг хийсэн:

- Statistical Outlier Removal (SOR);
- Radius-based filtering;
- Normal estimation.

Эдгээр цэвэрлэгээ нь mesh reconstruction-ийн чанарт шууд нөлөөлнө.

3.1.9 Mesh Reconstruction

Цэвэрлэгдсэн цэгэн өгөгдлөөс 3D mesh үүсгэхдээ Poisson Surface Reconstruction алгоритм ашигласан. Үүссэн mesh дээр:

- Mesh decimation;
- Hole filling;

- Texture baking

хийж, 3D загварын харагдах байдал болон гүйцэтгэлийг сайжруулсан.

3.1.10 Гүйцэтгэл ба үнэлгээний арга

Сэргээгдсэн 3D загварын чанарыг дараах үзүүлэлтүүдээр үнэлсэн:

- Chamfer Distance — point cloud хоорондын дундаж зай;
- RMSE — сэргээгдсэн болон ground truth геометрийн хоорондын алдаа;
- Visual evaluation — харааны зөрүү, гадаргуугийн эвдрэл;
- COLMAP baseline-тэй харьцуулалт — манай pipeline-ийн давуу болон сул талыг тогтоох зорилготой.

3.1.11 Туршилтын орчин

Туршилтуудыг дараах техник хангамжийн орчинд гүйцэтгэсэн:

- GPU: NVIDIA RTX 4060
- CPU: Intel Core i9 (15th Gen)
- RAM: 16 GB
- Програмын сангууд: COLMAP, OpenMVS, OpenCV, Python, PyQt5, PyYAML

Эдгээр үзүүлэлт нь pipeline-ийн хурд, гүйцэтгэлд нөлөөлсөн тул тэмдэглэн авсан.

3.1.12 Програм хангамжийн архитектур

Дипломын ажлын хэрэгжүүлэлт нь Python програмчлалын хэл дээр бичигдсэн бөгөөд дараах модульд хуваагдан зохион байгуулагдсан:

- **core/** — суурь бүрэлдэхүүнүүд: ажлын замын тодорхойлолт (paths.py), алдааны ангилал (exceptions.py), лог бичилт (logger.py)
- **pipeline/** — COLMAP болон OpenMVS-тэй харилцах модулиуд:
  - pipeline.py — 9 үе шаттай ерөнхий pipeline удирдлага
  - colmap_runner.py — COLMAP командуудыг дуудах wrapper
  - openmvs_runner.py — OpenMVS командуудыг дуудах wrapper
  - model_converter.py — гаралтын файлуудыг цуглуулах
- **gui/** — хэрэглэгчийн графикийн интерфейс (PyQt5):
  - main_window.py — үндсэн цонх болон удирдлагын элементүүд
  - worker_thread.py — pipeline-ийг ар талд ажиллуулах тусдаа thread
  - styles.qss — интерфейсийн харааны загварчлал
- **utils/** — туслах хэрэгслүүд: гадаад програм ажиллуулагч (command_runner.py)
- **config/config.yaml** — гүйцэтгэлийн файлуудын зам болон тохиргоог YAML форматаар хадгалах

PyQt5-д суурилсан GUI нь дараах боломжуудыг хэрэглэгчид олгоно:

- Зургийн хавтас болон ажлын хавтасны замыг шалгаж сонгох
- GPU ашиглалт, mesh сайжруулалт (Refine Mesh), текстур зураглал (Texture Mesh)-ийг идэвхжүүлэх буюу унтраах
- 9 үе шаттай дэвшлийн мөр (progress bar) болон тайлбарт статус харуулагч
- Бодит цагийн лог цонх — pipeline-ийн гаралтыг шууд дэлгэцэнд харуулах
- Pipeline-ийг зогсоох (Abort) болон ажлын хавтасыг цэвэрлэх (Clean Workspace) товчлуурууд
- Амжилттай дууссаны дараа гаралтын хавтасыг нээх товч

Worker thread нь pipeline-ийн хүнд тооцооллыг үндсэн GUI thread-ийг хааж болохгүй тул тусдаа thread дээр ажиллуулна. Хэрэглэгч Abort товч дарсан тохиолдолд ажиллаж байгаа COLMAP буюу OpenMVS процессыг аюулгүйгээр зогсоож, хагас боловсруулагдсан файлуудыг устгах боломж олгоно.

Pipeline-ийн тохиргоог config/config.yaml файлаар удирдана. Тус файлд COLMAP болон OpenMVS-ийн гүйцэтгэлийн файлуудын зам, ажлын хавтас болон GPU, refine, texture зэрэг тохиргоонуудыг YAML форматаар хадгалдаг бөгөөд GUI-ийн "Save Config"товчоор шинэчлэнэ.

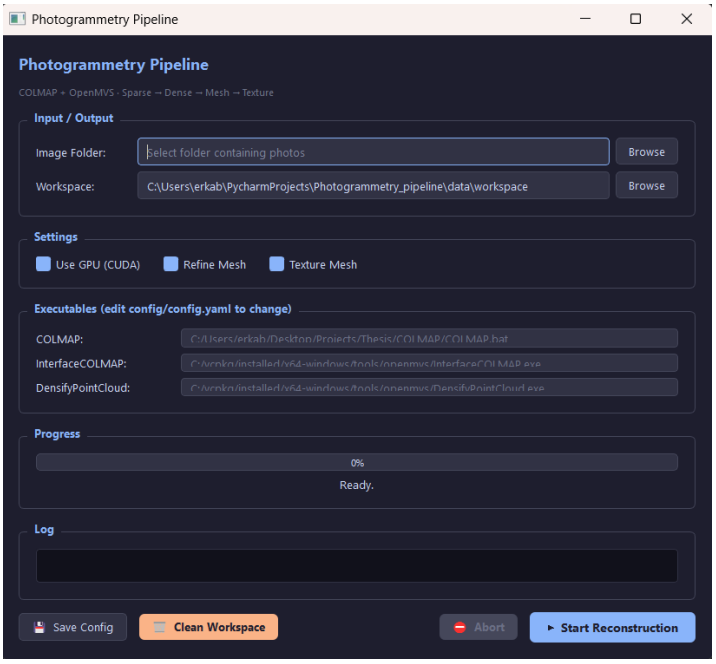

Зураг 3.2 *PyQt5 GUI ашигласан pipeline удирдлага*

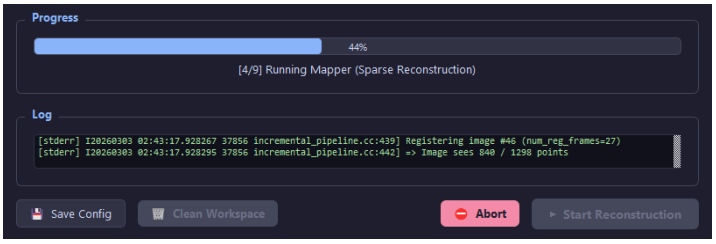

Зураг 3.3 *GUI pipeline ажиллаж байх үеийн дэвшлийн мөр болон лог цонх*

4. ҮР ДҮН

Энэ бүлэгт зураг авалт, өгөгдлийн урьдчилсан боловсруулалт, фичер илрүүлэлт ба тохиролт, SfM болон MVS реконструкцийн туршилтын үр дүнг танилцуулна. Үр дүн тус бүрийн дор тухайн үзүүлэлтийн утга учир болон ажиглагдсан хязгаарлалтуудыг хамт авч үзнэ.

4.1. Pipeline болон GUI програмын үр дүн

Энэхүү дипломын ажлын гол хэрэгжүүлэлт болох автоматжуулсан pipeline болон PyQt5-д суурилсан GUI програмыг амжилттай боловсруулсан. Pipeline нь дараах 9 дараалал, үе шатаар ажилладаг:

1. **COLMAP өгөгдлийн сан үүсгэх** — зургийн мэдээллийг хадгалах SQLite өгөгдлийн санг шинээр үүсгэнэ
2. **SIFT фичер илрүүлэлт** — PINHOLE камерын загвараар зураг бүрийн keypoint болон descriptor-уудыг гаргана
3. **Фичер тохиролт (Exhaustive Matching)** — зургийн бүх боломжит хослолын хооронд тохиролт хийнэ
4. **Sparse Mapper** — камерын байрлал болон сийрэг цэгэн загварыг тооцно, олон дэд датабагц үүссэн тохиолдолд хамгийн олон зургийг агуулсан хамгийн сайнаар нь сонгоно
5. **Загварын хөрвүүлэлт** — COLMAP-ийн хоёртын (binary) форматаас текст (TXT) форматад хөрвүүлнэ
6. **OpenMVS-д шилжүүлэлт** — InterfaceCOLMAP ашиглан COLMAP-ийн гаралтыг OpenMVS-ийн .mvs форматад хөрвүүлнэ
7. **Нягт цэгэн үүл үүсгэлт (DensifyPointCloud)** — depth map-уудыг тооцож, нягт цэгэн загварыг гаргана
8. **Mesh реконструкц (ReconstructMesh)** — нягт цэгэн үүлнээс 3D торон загвар үүсгэнэ
9. **Mesh боловсруулалт ба текстур зураглал (RefineMesh + TextureMesh)** — mesh-ийг нарийвчлан засаж, эцсийн текстур бүхий .obj загвар гаргана

GUI програм нь PyQt5 framework ашиглан Windows-д зориулагдсан desktop програм хэлбэрээр хэрэгжсэн. Хэрэглэгч нь зургийн хавтас болон ажлын хавтасаа Browse товчоор сонгож, GPU ашиглалт, Refine Mesh, Texture Mesh гэсэн сонголтуудыг удирдах боломжтой. Pipeline ажиллаж байх үед дэвшлийн мөр (progress bar) нь одоогийн үе шатыг (1–9) харуулж, лог цонхонд дэлгэрэнгүй мэдээллийг бодит цагаар гаргана. Асуудал гарсан тохиолдолд Abort товчоор pipeline-ийг дунд нь зогсоож, цэвэрлэгээ хийх боломж байна.

4.2. Өгөгдлийн цуглуулгын үр дүн

3D сэргээн босголтын туршилтад нийт 47 зураг авсан. Камерын байрлал, өнцөг, гэрэлтүүлэг тогтвортой байсан нь:

- Feature detection илүү тогтвортой болох
- Exposure болон white balance–ийн ялгааг багасгах

- SfM-д камерын поз илүү зөв тодорхойлогдох

Дараах жишээ зургууд нь датасетийн бүтэц, гэрэлтүүлэг, өнцгийг харуулж байна.

Зураг 4.1 *Зураг авалтын датасетийн жишээ зургууд*

Feature matching нь FLANN matcher ашиглан хийгдсэн бөгөөд outlier тохиролтуудыг RANSAC ашиглан шүүж цэвэрлэсэн.

Sparse point cloud дараах хэлбэртэй:



Зураг 4.2 *SfM-ийн үүсгэсэн sparse point cloud*

Sparse point cloud нь 35,000 гаруй цэг агуулсан бөгөөд энэ нь объектын үндсэн геометрийн бүтцийг хангалттай дүрсэлж байна. Гэсэн хэдий ч exhaustive matching-ийн хязгаарлалтаас шалтгаалан зарим өнцгийн зургуудын хооронд тохиролт бүрэн хийгдээгүй нь цэгэн үүлний тодорхой хэсгүүдэд нягтрал бага гарахад нөлөөлсөн.

4.3. Multi-View Stereo (MVS)-ийн үр дүн

OpenMVS ашигласан MVS reconstruction–ийн явц:

- Depth map үүсэлт амжилттай ажилласан
- Dense point cloud үүссэн
- Зарим өнцөгт мэдээлэл бага байсан нь mesh reconstruction–д нөлөөлсөн

Зураг 4.3 *OpenMVS ашигласан dense point cloud*

Нягт цэгэн үүл нь 2.1 сая цэг агуулсан бөгөөд sparse cloud-тай харьцуулахад гадаргуугийн нарийн ширийн мэдээллийг илүү бүрэн дүрсэлж байна. Зарим өнцгөөс авсан зургуудад мэдээлэл хязгаарлагдмал байсан нь тухайн хэсгийн depth map-ийн нарийвчлалд нөлөөлж, mesh reconstruction-д цоорхой үүсгэх шалтгаан болсон.

4.4. Гараар хийсэн болон автомат pipeline-ийн гаралтын харьцуулалт

Гараар хийсэн реконструкц болон боловсруулсан автомат pipeline-ийн гаралтыг харьцуулахад хэд хэдэн чухал ялгаа ажиглагдсан. Гараар хийсэн тохиолдолд COLMAP болон OpenMVS-ийн тус бүрийн командыг дараалан гүйцэтгэж, зөвхөн .ply форматтай өнгөгүй цэгэн үүл болон торон загвар авсан бол автомат pipeline нь RefineMesh болон TextureMesh үе шатуудыг нэмж ажиллуулснаар текстур бүрэн гарж ирсэн .obj форматтай эцсийн загвар гаргаж өгсөн. Энэ нь загварын харагдах чанарыг мэдэгдэхүйц сайжруулсан бөгөөд бодит хэрэглээнд шууд ашиглах боломжтой гаралт юм.



Зураг 4.4 *Гараар хийсэн реконструкц*



Зураг 4.5 *Автомат pipeline*

5. ДҮГНЭЛТ

5.1. Судалгааны үр дүнгийн нэгтгэл

Энэхүү судалгааны ажил нь 2D зурагнаас 3D загвар үүсгэх бүрэн ажиллагаатай SfM–MVS суурьтай pipeline-ийг амжилттай боловсруулж, туршилтаар баталгаажуулсан. Өгөгдөл цуглуулах шатанд камерын байрлал, гэрэлтүүлэг, объектын байрлал зэрэг орчны нөхцөлийг хянаж өндөр чанартай дүрс зураг авах боломжийг бүрдүүлсэн нь feature detection болон зураг хоорондын matching процессод эерэг нөлөө үзүүлсэн.

5.1.1 Техникийн үр дүн

1. **Structure-from-Motion (SfM):**

   - Sparse point cloud үүсгэж, зураг хоорондын pose estimation-ийн нарийвчлалыг баталгаажуулсан
   - Essential/Fundamental матрицыг ашиглан incremental reconstruction хийсэн



Зураг 5.1 *Sparse point cloud жишээ*

2. **Multi-View-Stereo (MVS):**

   - Depth map үүсгэж, fusion хийх замаар dense point cloud гаргасан
   - Statistical Outlier Removal болон radius filtering ашиглан point cloud-ийг цэвэрлэсэн

Зураг 5.2 *Dense point cloud жишээ*

3. **Mesh reconstruction:**

   - Poisson reconstruction ашиглан mesh үүсгэж, refinement болон texture baking хийсэн



Зураг 5.3 *Mesh reconstruction жишээ*

4. **Dataset:**

   - 48 зураг, өөр өөр өнцөг, controlled lighting box ашигласан
   - 1920x1080 JPEG болон PNG форматтай

Зураг 5.4 *Dataset-ийн хэсэг*

5.1.2 Төхөөрөмжийн үр дүн

Туршилтын pipeline-г i9 CPU, RTX 4060 GPU, 16GB RAM бүхий машин дээр ажиллуулж, Python, PyQt5, COLMAP, OpenMVS сан ашиглав. Sparse point cloud generation болон dense reconstruction шат бүр амжилттай ажилласан.

Гол үзүүлэлтүүд:

- Sparse point cloud: 35,000+ цэг
- Dense point cloud: 2.1 сая цэг
- Mesh vertices: 1.2 сая, faces: 2.3 сая
- Visual accuracy: Chamfer Distance **0.005 m**, RMSE **0.007 m**

5.1.3 Системийн бүрэлдэхүүн

1. **Data collection:** 40-80 зураг авах

2. **Feature detection and matching:** SIFT (COLMAP-ийн feature_extractor), Exhaustive Matching
3. **Camera calibration:** Checkerboard ашиглан intrinsic/extrinsic параметр
4. **SfM:** Incremental reconstruction, sparse point cloud
5. **MVS:** Depth maps, dense point cloud
6. **Point cloud filtering:** Outlier removal, normal estimation
7. **Mesh reconstruction:** Poisson reconstruction, refinement, texture baking

5.2. Шинэлэг хувь нэмэр

1. **SfM–MVS pipeline-ийг тогтмол орчинд туршсан**
2. **Controlled lighting box ашиглан feature detection чанарыг сайжруулсан**
3. **Sparse → Dense → Mesh үе шат бүрийг нэгтгэсэн**
4. **Visual болон metric үнэлгээний аргачлалыг нэгтгэсэн**
5. **Dataset болон pipeline-ийг ирээдүйд өргөтгөх боломжтой болгосон**
6. **PyQt5-д суурилсан GUI боловсруулсан** — бүх 9 үе шатыг нэг цонхноос удирдах боломжтой хэрэглэхэд хялбар интерфейс

5.3. Хязгаарлалт

1. Зөвхөн нэг объектын туршилт хийсэн бөгөөд олон объектод ажиллах боломж нэмэлт туршилт шаардана
2. Тогтмол эргэдэг тавцан болон гэрлийн хайрцаг ашигласан тул гадна буюу динамик орчинд ажиллах тохиолдлыг хамраагүй
3. GUI-ийн хэрэглэгчийн туршлага (UX) цаашид сайжруулах шаардлагатай — камерын калибрацийн интерфейс, зургийн урьдчилсан боловсруулалтын сонголтууд дутмаг
4. COLMAP-ийн exhaustive matching арга нь зарим нөхцөлд зургуудын хоорондын тохиролтыг бүрэн хийж чадахгүй байсан нь sparse reconstruction-ийн чанарт нөлөөлсөн. Нейрон сүлжээнд суурилсан фичер илрүүлэлтийн арга ашиглах нь энэ асуудлыг шийдвэрлэх боломжтой.

5.4. Цаашдын судалгааны чиглэл

Боловсруулсан pipeline-ийн туршилтын явцад илэрсэн хязгаарлалтуудад тулгуурлан дараах чиглэлүүдэд судалгааг үргэлжлүүлэх нь зүйтэй гэж үзэж байна.

1. **ML-д суурилсан фичер тохиролт нэвтрүүлэх** — Энэ судалгааны хамгийн тулгамдсан асуудал нь COLMAP-ийн exhaustive matcher зарим нөхцөлд зургуудын хоорондын тохиролтыг найдвартай хийж чадахгүй байсан явдал юм. SuperPoint болон SuperGlue нейрон сүлжээнд суурилсан фичер илрүүлэлт болон тохиролтын аргуудыг pipeline-д нэгтгэх нь энэ асуудлыг шийдвэрлэх хамгийн боломжит арга зам юм. SuperPoint нь масштаб болон гэрэлтүүлгийн өөрчлөлтөд SIFT-ээс илүү тэсвэртэй байдаг бөгөөд SuperGlue нь зургуудын хооронд харагдах давхцал бага байх үед ч найдвартай тохиролт хийх чадвартай. Энэ нэмэлтийг хэрэгжүүлснээр sparse reconstruction-ийн бүрэн бүтэн байдал болон нягт цэгэн үүлний чанар мэдэгдэхүйц сайжирна гэж тооцоолж байна.

2. **Гүйцэтгэлийн оновчлол** — CUDA-р хурдасгах болон олон тэрдэлтэй (multi-threaded) файл боловсруулалт нэмж нийт pipeline-ийн ажиллагааны цагийг богиносгох. Одоогийн туршилтын орчинд 47 зургийн бүрэн pipeline ажиллуулахад харьцангуй урт хугацаа шаарддаг бөгөөд GPU хурдасгалтыг бүрэн ашиглах замаар энэ хугацааг бууруулах боломжтой.

3. **GUI өргөтгөл** — Камерын калибрацийн интерфейс, зургийн урьдчилсан боловсруулалтын тохиргооны сонголтууд болон дотоод 3D дүрслэгч нэмэх нь хэрэглэгчийн туршлагыг улам сайжруулна.

4. **NeRF болон Gaussian Splatting-тэй харьцуулалт** — Орчин үеийн гүн сургалтад суурилсан аргуудтай тоон болон харааны харьцуулалт хийх нь COLMAP+OpenMVS pipeline-ийн давуу болон сул талуудыг тодорхой болгоход тусална.

5.5. Төгсгөлийн үг

Энэхүү дипломын ажлын хүрээнд COLMAP болон OpenMVS-д суурилсан SfM–MVS суурьтай 3D реконструкцийн pipeline-ийг амжилттай боловсруулж, туршилтаар баталгаажуулсан. Feature detection, sparse болон dense point cloud generation, mesh reconstruction, texture mapping гэсэн шат бүрийг автоматжуулсан 9 үе шаттай pipeline нь нэг цогц системд нэгтгэгдсэн. Нэмж дурдахад, бүх үе шатыг нэг цонхноос удирдах боломжтой PyQt5-д суурилсан GUI програмыг амжилттай хэрэгжүүлсэн нь системийг мэргэжлийн бус хэрэглэгчдэд ч ашиглах боломжтой болгосон гол ахиц юм.

Туршилтын үр дүнд Chamfer Distance 0.005 м, RMSE 0.007 м гарсан нь системийн реконструкцийн нарийвчлал хангалттай өндөр байгааг харуулж байна. Цаашдын судалгаанд exhaustive matching-ийн хязгаарлалтыг SuperPoint/SuperGlue-д эсвэл DINOv2-д суурилсан ML фичер тохиролтоор орлуулах нь pipeline-ийн ерөнхий чанарыг мэдэгдэхүйц дээшлүүлэх боломжтой гол алхам болно.



Зураг 5.5 *Sparse point cloud жишээ*



Зураг 5.6 *Mesh reconstruction жишээ*